Suomen ympäristökeskus
Finlands miljöcentral
Finnish Environment Institute

Ohje kaavahakemiston (VOOKA-aineisto) tallentamiseen ja päivittämiseen Ryhti-järjestelmään Ryhti-palvelun käyttöliittymällä

25.3.2026

Suomen ympäristökeskus | Finlands miljöcentral | Finnish Environment Institute
Latokartanonkaari 11 | 00790 Helsinki | FINLAND
+358 295 251 000 | mailto: kirjaamo@syke.fi | Y-tunnus 0996189-5 | **syke.fi**

Sisällys

1. Johdanto 3
2. Kirjautuminen Ryhti-palveluun 3
3. Kaavan perustietojen muuttaminen ja täydentäminen....4
4. Uuden kaavan tuominen Ryhti-järjestelmään....5
4.1. Pysyvän kaavatunnuksen hakeminen....5
5. Aiemmin tallennetun tiedoston poistaminen ja uuden tiedoston lisäys tallennetetulle kaava-asialle 8
5.1. Kirjaudu palveluun ja valitse muokattava asia....8
5.2. Vaiheen valitseminen....9
5.3. Tiedoston poistaminen....9
6. VOOKA-kaavan voimassaoloajan alkamisajankohta ja hyväksymispäivämäärän päivitys 11
7. Kaavan JSON-tiedoston päivitys....13
8. Kaavan rajauksen päivittäminen Ryhti-järjestelmään ilman kumoutumista 15
9. Uudella VOOKA-kaavalla kumotaan alle jäävät VOOKA-kaavat kokonaan tai osittain....17
9.1. Kaavan avaimen eli planKeyn hakeminen ja muodostaminen 17
10. Uusi kaava kumoaa yhden kaavan kokonaan tai osittain 18
11. Uusi kaava kumoaa useamman kaavan kokonaan tai osittain 20
12. Kaava on kumottu erillisellä päätöksellä....22
12.1. Lisää uusi vaihe....22
12.2. Elinkaarentila kumoutunut 22
12.3. Lisää vaiheen aluerajaus (sama kuin voimassa vaiheella)....23
12.4. Täytä päätöksen tiedot 23

Suomen ympäristökeskus | Finlands miljöcentral | Finnish Environment Institute
Latokartanonkaari 11 | 00790 Helsinki | FINLAND
+358 295 251 000 | mailto: kirjaamo@syke.fi | Y-tunnus 0996189-5 | syke.fi

1. Johdanto

Tässä ohjeessa käydään läpi, miten VOOKA-tasoista kaavahakemistoaineistoa tallennetaan ja päivitetään Ryhti-palvelun käyttöliittymässä.

Ryhti-palvelun käyttöliittymän kautta voi tallentaa kaavahakemistoaineiston eli kaavan rajauksen ja siihen liittyvät asiakirjat. Palvelussa on mahdollista tallentaa kaavoja kuitenkin vain yksi kerrallaan. Koko kunnan kaavahakemiston tallentaminen yhdellä tallennuksella ei ole mahdollista.

Ohjeita kaavahakemistoaineiston tekemiseen löytyy verkkosivulta https://ryhti.syke.fi/alueidenkaytto/voimassa-olevat-kaavat-tietojarjestelmaan/vooka-ohje-kunnille/.

2. Kirjautuminen Ryhti-palveluun

Kaavatietoja pääsee tallentamaan Ryhti-palvelun käyttöliittymän kautta, jonka osoite on https://ryhti-palvelut.syke.fi/. Kirjaudu palveluun oikean yläreunan *kirjaudu*-painikkeesta.

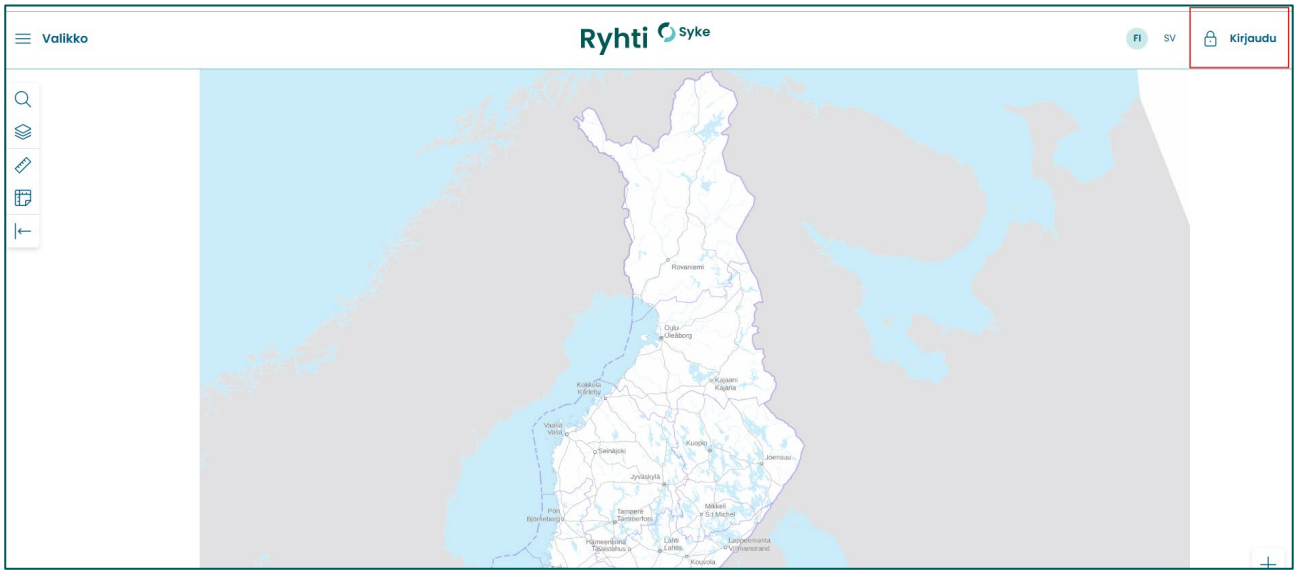

Kuva 1: Palveluun kirjaudutaan oikean yläreunan linkistä.

Ennen kuin aloitat palvelun käytön, on hyvä varmistaa, että kunnalla on Suomen ympäristökeskuksen myöntämä lupa tietojen tallentamiseen rakennetun ympäristön tietojärjestelmään. Lisäksi palvelua käyttävä henkilö tarvitsee Suomi.fi-valtuuden, jonka nimi on rakennetun ympäristön alueidenkäyttötietojen ilmoittaminen. Valtuuden myöntää kunta.

Lisätietoa luvasta ja kirjautumisesta
Ohjeet Ryhti-järjestelmän viranomaispalveluiden käyttöön

Suomen ympäristökeskus | Finlands miljöcentral | Finnish Environment Institute
Latokartanonkaari 11 | 00790 Helsinki | FINLAND
+358 295 251 000 | mailto: kirjaamo@syke.fi | Y-tunnus 0996189-5 | syke.fi

3. Kaavan perustietojen muuttaminen ja täydentäminen

Lomakkeella *Perustiedot*-välilehdellä voi muokata esimerkiksi kaavan nimen, kaavalajin, kuvauksen sekä vireilletulopäivämäärän. Pakolliset tiedot on merkitty tähdellä.

Kaavalajin voi muuttaa saman kaavatason sisällä, jos se on aiemmin tallennettu väärin. Esimerkiksi asemakaava voi muuttua ranta-asemakaavaksi.

Kaava-asian nimen voi muuttaa tai lisätä tarvittaessa esimerkiksi ruotsinkielisen nimen. Kaava-asian nimi näytetään karttapalvelussa. Hankenimeä, jolla kaavatunnus on haettu, ei näytetä karttapalvelussa vaan se näkyy ainoastaan organisaatiolle, joka tunnuksen on hakenut (katso kuvat 4 ja 7).

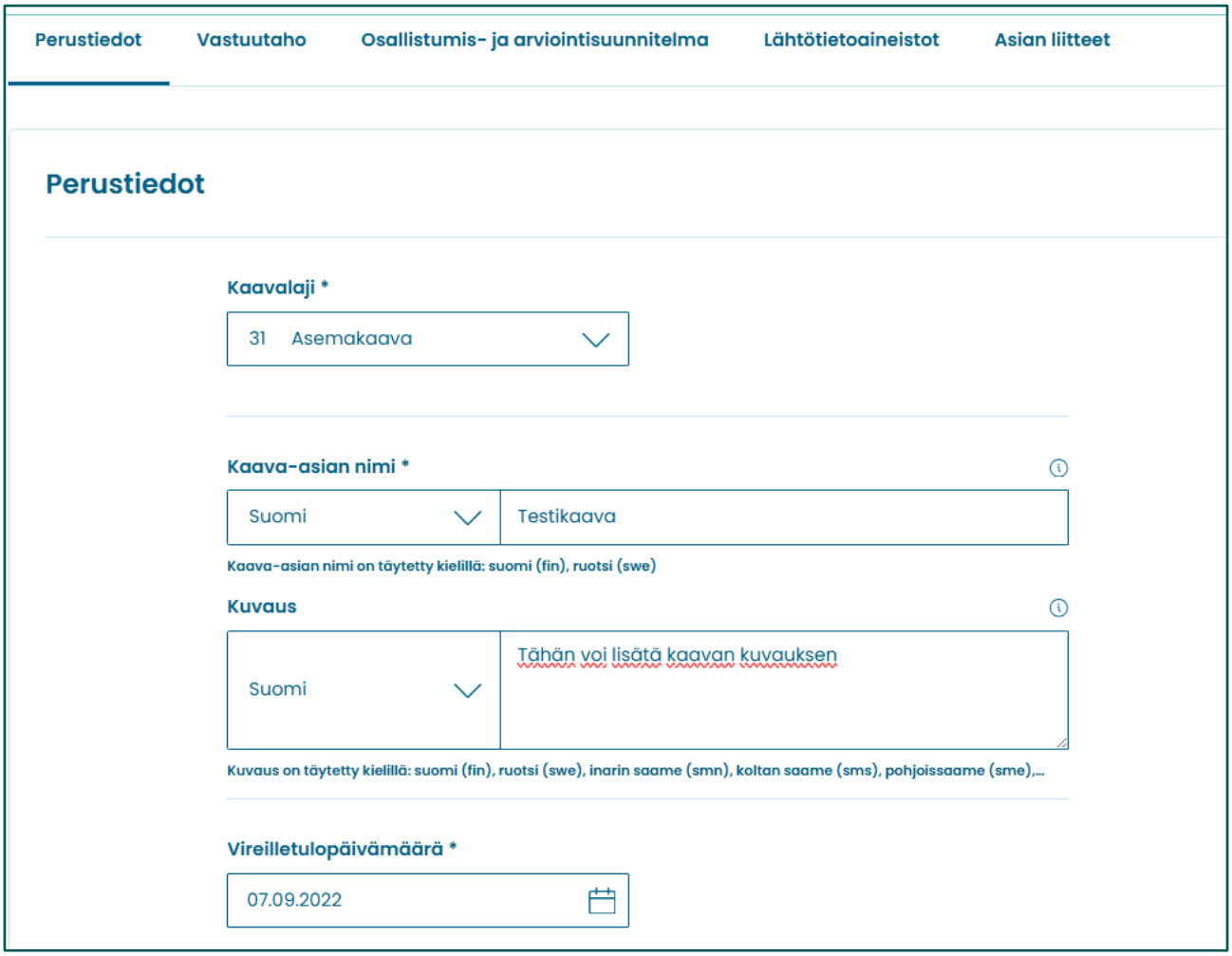

Kuva 2: Tietojen lisääminen Perustiedot-välilehdellä.

4. Uuden kaavan tuominen Ryhti-järjestelmään

4.1. Pysyvän kaavatunnuksen hakeminen

Aloita kirjautumalla Ryhti-palveluun ja valitse sen jälkeen sivuvalikosta kohta *Hae kaavalle pysyvä kaavatunnus.*

Kuva 3: Pysyvän kaavatunnuksen hakemiseen edetään vasemman reunan valikosta.

Pysyvän kaavatunnuksen hakemista varten valitaan kaavalaji. Alasvetovalikosta löytyy kaavalaji-koodiston mukainen listaus.

Kaavalajia voi myöhemmin muuttaa kaavatason sisällä. Tämä tarkoittaa, että myöhemmin voi muuttaa esimerkiksi asemakaavasta ranta-asemakaavaan, mutta ei esimerkiksi asemakaavasta yleiskaavaan tai maakuntakaavan. Pysyvän kaavatunnuksen alussa oleva kirjaintunnus kertoo kaavatason.

Kannattaa aina tarkistaa jo haetut kaavatunnukset ja varmistaa, ettei kyseiselle kaavalle ole vielä haettu pysyvää tunnusta.

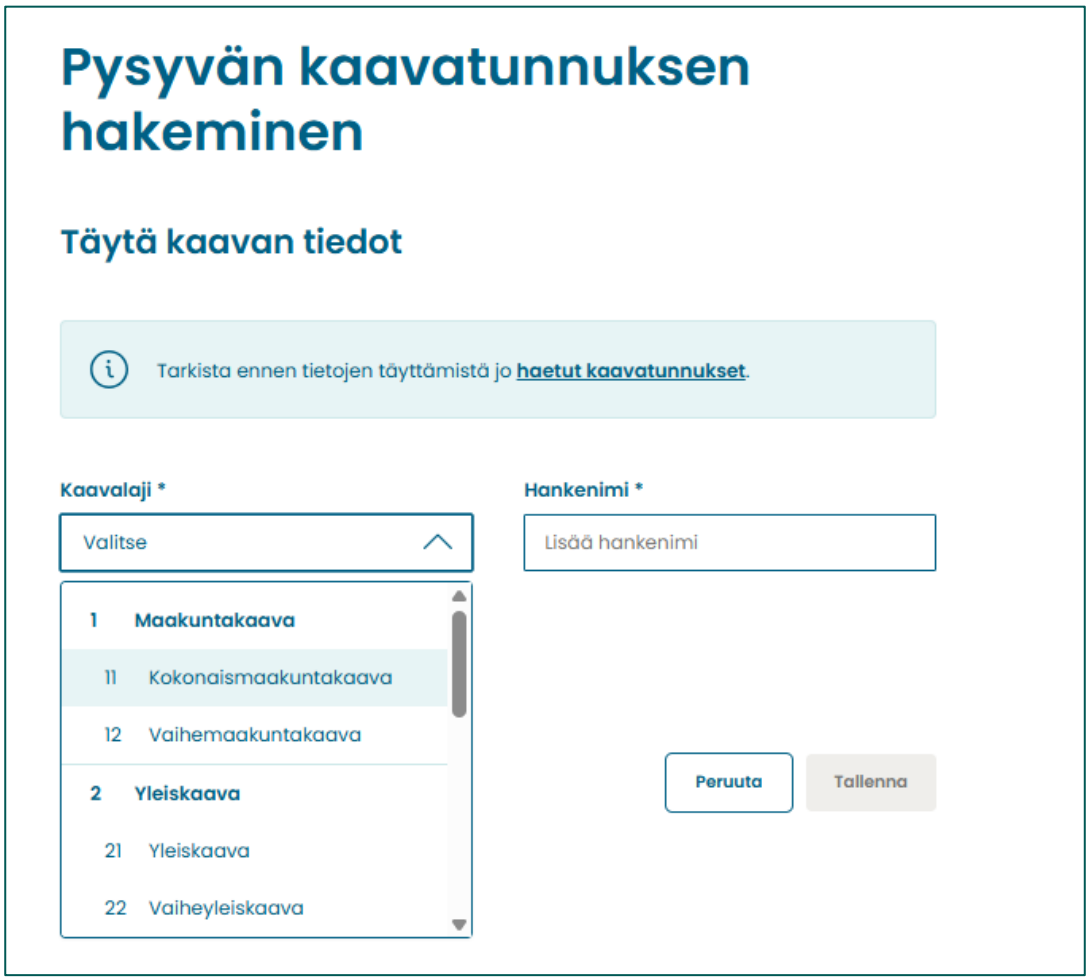

Kuva 4: Pysyvää kaavatunnusta haettaessa valitaan kaavalaji ja annetaan hankenimi. Annettu hankenimi ei näy muille kuin hakijakunnalle.

Kun halutaan tallentaa dokumentteja ja syöttää tiedot kaavasta lomakkeella, valitaan *Lisää aineisto lomakkeella*.

Kuva 5: Aineistoja voi tuoda JSON-tiedostona tai lomakkeen kautta.

Katso esimerkkitiedostot

Kaavarajaus: *kaava-asian_aluerajaus.json*
Kaavarajauksen JSON-sanoman rakenne näkyy myös kuvassa 22.

Kaavat: *kaava.json, AK-kaava_pvm.json, YK-kaava_pvm.json*
Kaavan JSON-sanoman rakenne näkyy myös kuvassa 23.

JSON-tiedostoa voi muokata eri ohjelmilla. Esim. Visual Studio Code tai Notepad.

Suomen ympäristökeskus | Finlands miljöcentral | Finnish Environment Institute
Latokartanonkaari 11 | 00790 Helsinki | FINLAND
+358 295 251 000 | mailto: kirjaamo@syke.fi | Y-tunnus 0996189-5 | **syke.fi**

5. Aiemmin tallennetun tiedoston poistaminen ja uuden tiedoston lisäys tallennetetulle kaava-asialle

5.1. Kirjaudu palveluun ja valitse muokattava asia

Jo tuodulle kaavalle voidaan lisätä ja päivittää lomakkeella tiedostoja. Aiemmin tuotujen tiedostojen poisto on mahdollista. Aloita kirjautumalla Ryhti-palveluun ja sen jälkeen valitse sivuvalikosta *Tallenna tai validoi kaava-asia*.

Kuva 6: Valikosta valitaan tallenna tai validoi kaava-asia.

Valitse luettelosta kaava-asia, jonka tietoja haluat korjata tai päivittää. Voit hyödyntää hakusanalla hakemista tai järjestää luettelon esimerkiksi kaavatunnuksen, hankenimien tai *luotu*-sarakkeen mukaan painamalla otsikkoa.

Kuva 7: Kaava-asioiden luettelosta valitaan kaava-asia, jonka tietoja palvelussa halutaan tallentaa.

5.2. Vaiheen valitseminen

Valitse *kaava-asian vaiheet* -otsikon alta vaihe, jonka tiedostoja haluat päivittää. Huomioithan, että jos kaavasta on aiemmin kumottu päätöksellä osa, niin voimassaolovaiheita voi olla useampi kuin yksi.



Kuva 8: Vaiheista valitaan se, jonka tiedostoja halutaan päivittää.

5.3. Tiedoston poistaminen

Jo tuodun tiedoston voi poistaa käyttöliittymässä kolmen pisteen takaa. Uuden asiakirjan sekä sen tiedot pääset täyttämään painamalla *lisää uusi liiteasiakirja* -painiketta.

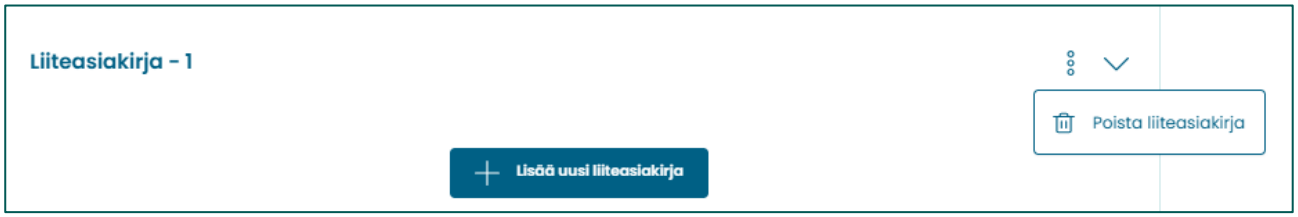

Kuva 9: Liiteasiakirjan poistoon ja lisäämiseen on omat valintakohtansa.

Pakolliset tiedot on merkitty tähdellä (*). Tiedot, joihin liittyy koodisto, on toteutettu alasvetovalikkona. Liiteasiakirjan pakollisia tietoja ovat asiakirjan laji, asiakirjan tunnus, asiakirjan nimi, henkilötietosisältö, julkisuusluokka, säilytysaika, asiakirjan päivämäärä ja kieli.

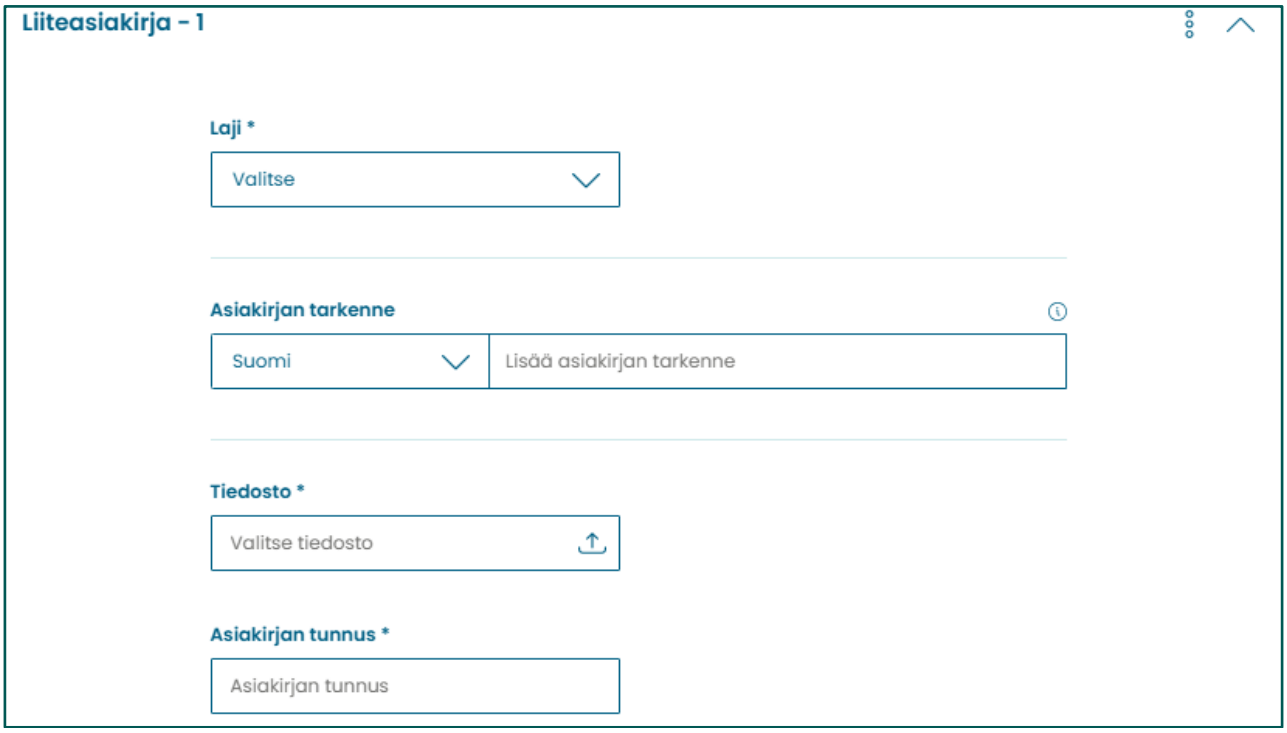

Kuva 10: Pakolliset täytettävät tiedot on merkitty tähdellä.

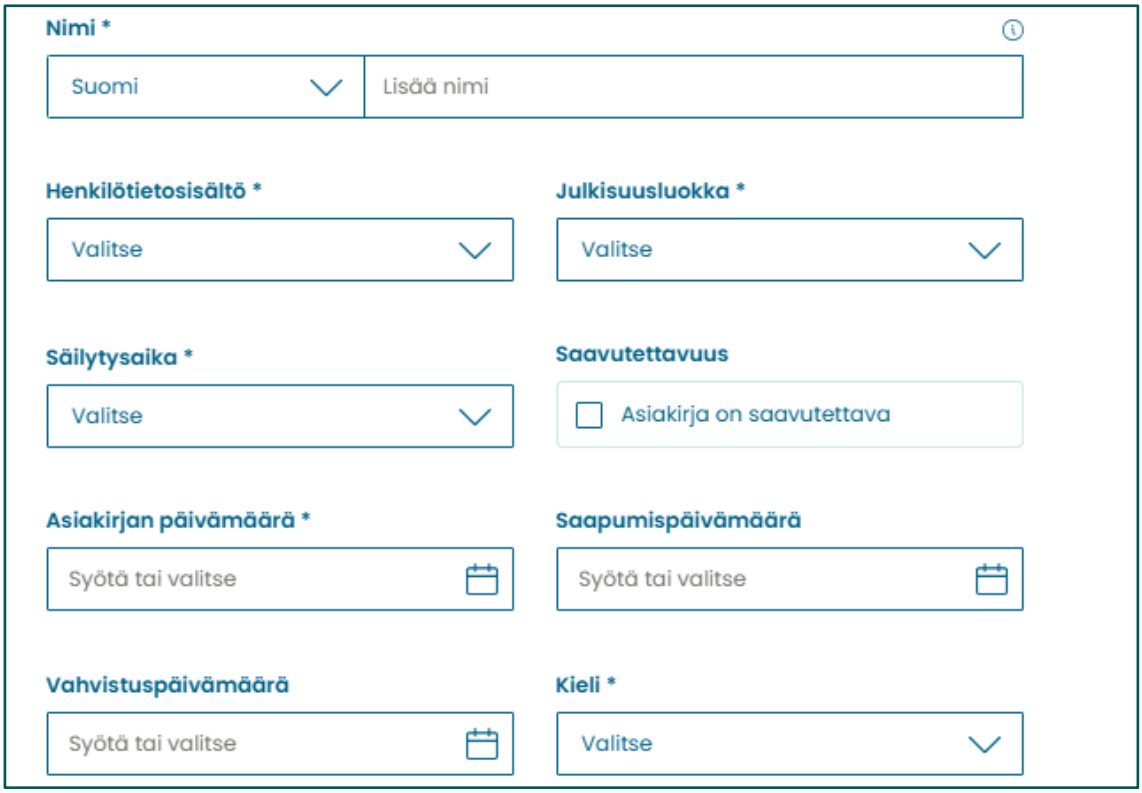

Kuva 11: Liiteasiakirjaan liittyviä täytettäviä tietoja.

6. VOOKA-kaavan voimassaoloajan alkamisajankohta ja hyväksymispäivämäärän päivitys

Ryhti-järjestelmään tallennetun kaavarajauksen voi hakea avoimelta kaavahakemisto-rajapinnalta.

Rajapintojen osoitteet

Tuotantoympäristön osoite:
https://paikkatiedot.ymparisto.fi/geoserver/ryhti_plan/ogc/features/v1

Testiympäristön osoitteet:
http://ixgstest1.ymparisto.fi/geoserver/ryhti_plan/ogc/features/v1
http://ixgstest1.ymparisto.fi/geoserver/ryhti_plan/wfs

Muodosta yhteys rajapintaan esimerkiksi QGIS-ohjelmistolla tai jollain muulla paikkatieto-ohjelmalla.

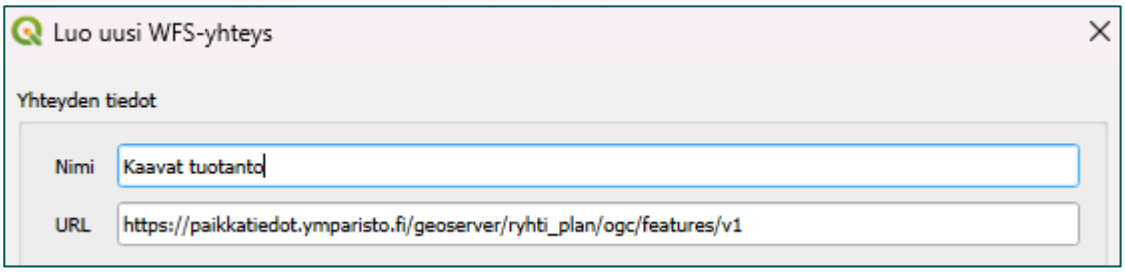

Kuva 12: Esimerkki rajapinnan avaamisesta QGIS-ohjelmistossa.

Haetaan kaavat paikkatietorajapinnalta ja valitaan kaava, jonka tiedot päivitetään. Tallenna kohde esimerkiksi geojson-muotoon.

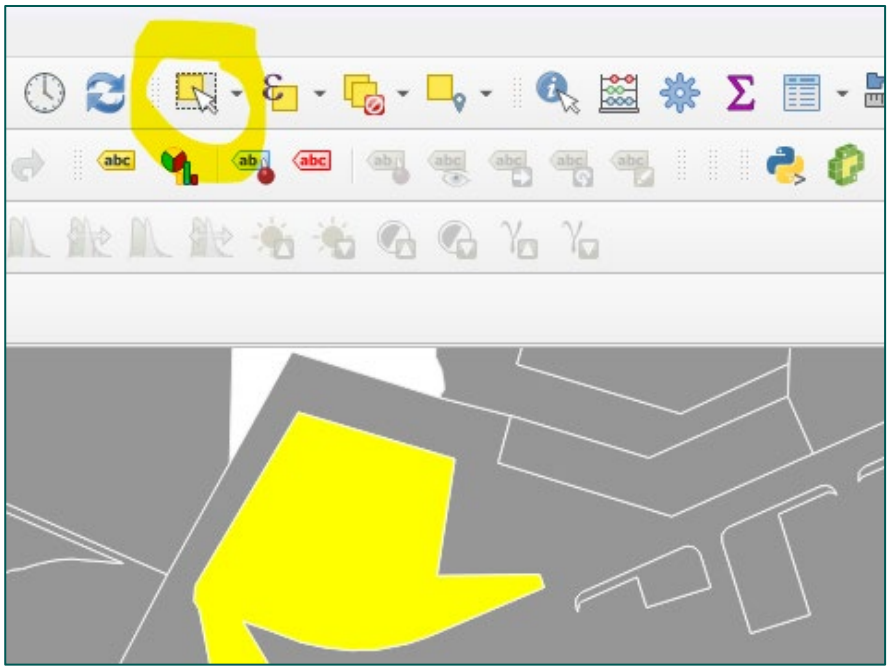

Kuva 13: Esimerkki QGIS-ohjelmistosta

Voit kopioida tallentamastasi tiedostosta (esim. GeoJSON) koordinaatit sekä geometrian tyypin (esim. polygon) ja koordinaatiston (3067) Ryhti-järjestelmään toimitettavaan kaavarajauksen JSON-tiedostoon.


```
{
"type": "FeatureCollection",
"name": "testi_",
"crs": { "type": "name", "properties": { "name": "urn:ogc:def:crs:EPSG::3067" } },
"features": [
{ "type": "Feature", "properties": { "id": "a61c0525-618b-4aac-95cf-dfe3a611990e", "plan_key": "3766f65a-
d999-49a5-8312-64120008c7f0", "permanent_plan_identifier": "AK-004503", "producer_plan_identifier": "894",
"plan_type": "http://uri.suomi.fi/codelist/rytj/RY_Kaavalaji/code/31", "plan_type_name_fin": "Asemakaava",
"original_administrative_area_identifiers": "[\\491\\]", "administrative_area_identifiers": "[\\491\\]",
"name_fin": "1. kaupunginosa Savilahti, kortteli 7", "name_swe": null, "name_eng": null, "name_smn": null,
"name_sms": null, "name_sme": null, "description_fin": "Aluerajaus ja asiakirjat kunnalta", "description_swe":
null, "description_eng": null, "description_smn": null, "description_sms": null, "description_sme": null,
"case_identifiers": [ ], "record_numbers": [ ], "time_of_initiation": "1900-01-01", "digital_origin":
"http://uri.suomi.fi/codelist/rytj/RY_DigitaalinenAlkupera/code/04", "date_of_validity": "1900-01-01",
"approval_date": "2011-12-12", "plan_life_cycle_status":
"http://uri.suomi.fi/codelist/rytj/kaavaelinkaari/code/13", "period_of_validity_begin": "1900-01-01",
"period_of_validity_end": null, "documents": "[{\\uri\\:
\\https://uri.rakennetunymparistontietojarjestelma.fi/planattachmentdocument/00809410-
b518-4880-9e8b-32a5705d500f/file\\,\\name_eng\\:null,\\name_fin\\:\\Kaavakartta ja kaavam\\u00E4\\u00E4r
\\u00E4ykset, 491-31-05-894-1.pdf\\,\\name_sme\\:null,\\name_smn\\:null,\\name_sms\\:null,\\name_swe\\:null,
\\file_content_type\\:\\application/pdf\\,\\type_of_attachment\\:
\\http://uri.suomi.fi/codelist/rytj/RY_AsiakirjanLaji_YKAK/code/05\\}]", "plan_type_code_value": 31,
"plan_life_cycle_status_code_value": 13, "permanent_binding_plot_division_identifier": [ null ] }, "geometry":
{ "type": "Polygon", "coordinates": [ [ [ 514363.667734159971587, 6839389.876721340231597 ],
[ 514396.079064449993894, 6839509.122503940016031 ], [ 514383.573368720011786, 6839512.60111194010824 ],
[ 514281.511609759996645, 6839539.874698139727116 ], [ 514248.863374279986601, 6839420.406204650178552 ],
[ 514363.667734159971587, 6839389.876721340231597 ] ] ] } }
]
}
```


Kuva 14: Esimerkki kaavarajauksen GeoJSON-tiedostosta.

Jos halutaan muokata kaavan rajausta, pitää myös kaava-asian rajaus päivittää vastaamaan kaavan rajausta. Lomakkeella kohta *Lisää kaava-asian aluerajaus*, kun tuodaan uusi kaava-asian aluerajaus JSON-tiedostona. Aiempaa rajausta ei tarvitse erikseen poistaa, vaan päälle tuodaan uusi korjattu rajaus.

Kuva 15: Kaava-asian aluerajauksen lisääminen


```
{
"srid": "3067",
"geometry": {
"type": "Polygon",
"coordinates":  [ [ [ 514363.667734159971587, 6839389.876721340231597 ], [ 514396.079064449993894,
6839509.122503940016031 ], [ 514383.573368720011786, 6839512.60111194010824 ], [ 514281.511609759996645,
6839539.874698139727116 ], [ 514248.863374279986601, 6839420.406204650178552 ], [ 514363.667734159971587,
6839389.876721340231597 ] ] ] |
 }
}
```


Kuva 16: Esimerkki kaavarajauksen JSON-tiedostosta

7. Kaavan JSON-tiedoston päivitys

Vie koordinaatit JSON-tiedostoon "geographicalArea" [ ] -hakasulkeiden sisälle.

Päivitä kaavan JSON-tiedostossa Voimassaoloaika "periodOfValidity" -kohtaan ja Hyväksymispäivämäärä "approvalDate" -kohtaan.


```
{
  "planKey": "f8224e95-7b8f-42b0-8346-b740ec6cffb1",
  "lifeCycleStatus": "http://uri.suomi.fi/codelist/rytj/kaavaelinkaari/code/13",
  "scale": 1000,
  "geographicalArea": {
  "srid": "3067",
  "geometry": {
  "type": "Polygon",
  "coordinates": [ [ [ 514363.667734159971587, 6839389.876721340231597 ], [ 514396.079064449993894,
6839509.122503940016031 ], [ 514383.573368720011786, 6839512.60111194010824 ],
[ 514281.511609759996645, 6839539.874698139727116 ], [ 514248.863374279986601,
6839420.406204650178552 ], [ 514363.667734159971587, 6839389.876721340231597 ] ] ]
    }
    },
  "periodOfValidity": {
  "begin": "1801-03-30"
   },
  "approvalDate": "1800-01-01"
   }
```


Kuva 17: JSON-tiedostossa asemakaavan esimerkkirakenne. Keltaisella on merkitty koordinaatisto, geometrian tyyppi sekä päivämääräkohdat.

Esimerkki-JSON-tiedostot

Kaavat: *AK-kaava_pvm.json, YK-kaava_pvm.json*

JSON-tiedostoa voi muokata eri ohjelmilla. Esim. Visual Studio Code tai Notepad.

Vie JSON-tiedosto *Lisää uusi kaava* -kehykseen ja valitse *Tallenna Ryhtiin*.

Kuva 18: JSON-tiedoston lisääminen

Tiedot päivittyvät heti lomakkeelle.

Kuva 19: JSON-tiedostosta tiedot päivittyvät lomakkeelle.

Karttakäyttöliittymässä kaavan päivitetyt tiedot näkyvät viimeistään noin 15 min kuluttua.

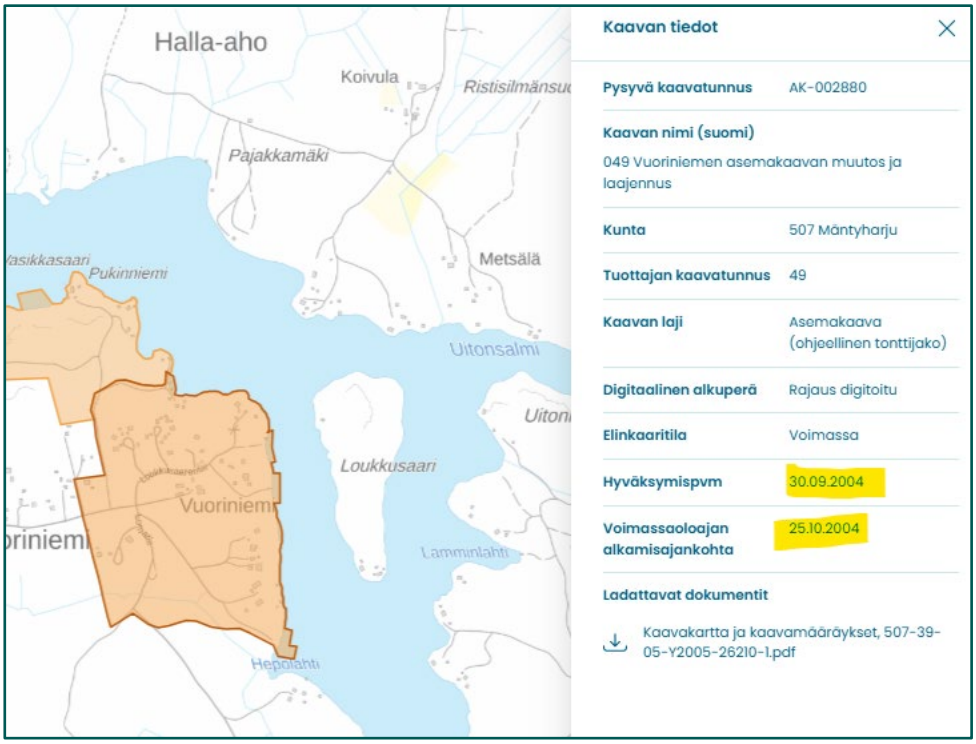

Kuva 20: Esimerkki tietojen näkymisestä Ryhti-palvelun kartalla

8. Kaavan rajauksen päivittäminen Ryhti-järjestelmään ilman kumoutumista

Kaavarajausta on mahdollista päivittää, jos kaava on tallennettu vain hakemistomuodossa eli digitaalinen alkuperä on *04 kaavarajaus digitoitu* tai *0401 -Rajaus useamman kunnan alueella*. Tämä voi tulla kyseeseen, jos Ryhti-järjestelmässä rajaus on väärin.

Rajauksen päivittäminen on mahdollista vain, jos saman kaavan alueella ei ole muita voimassaolevia saman kaavatason kaavoja. Tällöin voidaan päivittää voimassaolovaihetta tuomalla siihen uusi kaava-asian rajaus sekä kaava-aineisto.

Ryhti-järjestelmä validoi, että voimassaolovaiheessa kaava-asian aluerajaus ja kaavan aluerajaus ovat samassa koordinaatistossa ja rajaukset samat.

Kuva 21: Kaavan vaiheen aluerajauksen tuonti

Tallenna kaava-asian aluerajaus JSON-muodossa (*kaava-asian_aluerajaus.json*).


```
{
  "srid": "3067",
  "geometry": {
    "type": "Polygon",
    "coordinates": [
      [
       [ 376895.413716607959941, 6670011.78399389795959 ], [
376895.413716608076356, 6670185.051267450675368 ], [ 377094.834540888376068,
6670185.051267450675368 ], [ 377094.834540888376068, 6670011.783993900753558 ],
[ 376895.413716607959941, 6670011.78399389795959 ]

      ]
    ]
  }
}
```


Kuva 22: Aluerajaus JSON-muodossa

Kaavaluokalle tallennetaan JSON-tiedosto, jossa on sama geometria kuin kaavan vaiheella.


```
            {
                "planKey": "46877e24-6cd0-4534-a863-755417bc9002",
                "lifeCycleStatus": "http://uri.suomi.fi/codelist/rytj/kaavaelinkaari/code/13",
                ],
                "scale": 10000,
                "geographicalArea": {
                   "srid": "3067",
                   "geometry": {
                      "type": "Polygon",
                      "coordinates": [ 376895.413716607959941, 6670011.78399389795959 ], [
376895.413716608076356, 6670185.051267450675368 ], [ 377094.834540888376068,
6670185.051267450675368 ], [ 377094.834540888376068, 6670011.783993900753558 ], [
376895.413716607959941, 6670011.78399389795959 ]
                   }
                },                    "periodOfValidity": {
                   "begin": "2025-11-13"
                },
                "approvalDate": "2025-03-17"
             }
```


Kuva 23: Esimerkki kaava-JSONista (kaava.json)

9. Uudella VOOKA-kaavalla kumotaan alle jäävät VOOKA-kaavat kokonaan tai osittain

Kun rakennetun ympäristön tietojärjestelmään (Ryhti) tallennetaan uusi kaava elinkaaren tilassa *voimassa* – joko kaavahakemistomuodossa (sisältäen vain kaavan rajauksen ja asiakirjat) tai kokonaisena tietomallimuodossa – voidaan samalla tallentaa myös tieto niistä kaavoista, jotka uusi kaava kumoaa.

Uuden kaavan tallennussanomassa voi olla mukana kumoamistieto, jossa on alle jäävän kaavan tiedot. Jos alle jäävästä kaavasta on tuotu vain kaavarajaus (VOOKA-aineisto), Ryhti-järjestelmä päivittää kaavahakemistorajapinnalle uuden voimaan jäävän aluerajauksen. Tämä tehdään Ryhti-järjestelmässä leikkaamalla aiemmin tuodusta kaavarajauksesta uuden kaavan päälle menevä alue pois. Kunnan ei tarvitse erikseen toimittaa jäljelle jäävää kaavarajausta.

9.1. Kaavan avaimen eli planKeyn hakeminen ja muodostaminen

Jokaiselle uudelle VOOKA-kaavalle tulee antaa "planKey" ja "planCancellationInfoKey" -eli käyttämätön GUID-/UUID-tunniste. Tunnisteen voi hakea esimerkiksi täältä: https://www.guidgenerator.com/

Esimerkki UUID-muodosta

"planKey": "c72acf6c-05ad-4b20-af00-ece460766343"
"planCancellationInfoKey": "efc58f2d-68b0-423b-b950-7c9e9f825b94"

Kun kumotaan uudella kaavalla alle jääviä kaavoja, tulee kaavan JSON-sanomassa olla mukana kumoutumistieto eli "plancancellation info".

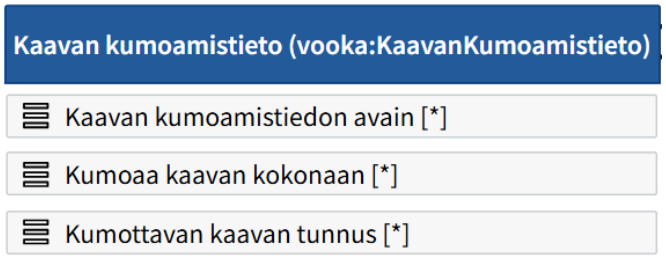

Kuva 24: Kumoutumistietoluokka VOOKA-soveltamisprofiilissa

Kaava, joka kumoutuu kokonaan, on kumoutumistiedoissa "cancelsEntirePlan": true. Osittain kumoutuva kaava "cancelsEntirePlan": false. Jos alle jäävä VOOKA-kaava kumoutuu osittain, Ryhti-järjestelmä leikkaa kaavalle geometrian, joka jää voimaan.

10. Uusi kaava kumoaa yhden kaavan kokonaan tai osittain

Ryhti-palvelun lomakkeella numeroidut kohdat 1 ja 5.

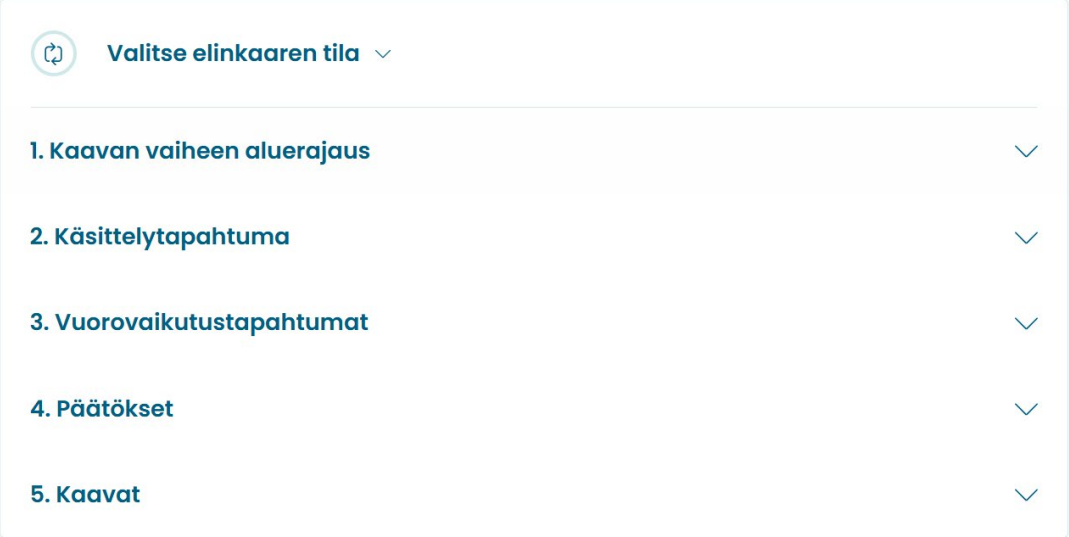

Kuva 25: Kuvakaappaus Ryhti-palvelun lomakenäkymästä.

Tallenna kaavavaiheelle asian aluerajaus JSON-muodossa. Tallennettaessa uusi vaihe tuodaan aina myös kaava-asian rajaus.


```
{
  "srid": "3067",
  "geometry": {
    "type": "Polygon",
    "coordinates": [
      [
       [ 376895.413716607959941, 6670011.78399389795959 ], [
376895.413716608076356, 6670185.051267450675368 ], [ 377094.834540888376068,
6670185.051267450675368 ], [ 377094.834540888376068, 6670011.783993900753558 ],
[ 376895.413716607959941, 6670011.78399389795959 ]

      ]
    ]
  }
}
```


Kuva 26: Esimerkki JSON-sanomasta aluerajaukselle

Tuodaan uusi kaava-JSON, joka kumoaa alle jäävän VOOKA-kaavan kokonaan tai osittain. Siinä tulee olla mukana kumoamistieto kumottavasta kaavasta. Kumoamistietoja varten tarvitaan kumottavan kaavan planKey.

Kumoutumistietoihin tarvittavan kaavan avain URIn voi hakea Ryhdin karttapalvelusta https://ryhti-palvelut.syke.fi/ . Kaavan avain URI voidaan kopioida kaavahakemisto tasolta valitsemalla haluttu kaava ja sivupalkista kaavan tiedot kohdasta kolmen pisteen takaa.

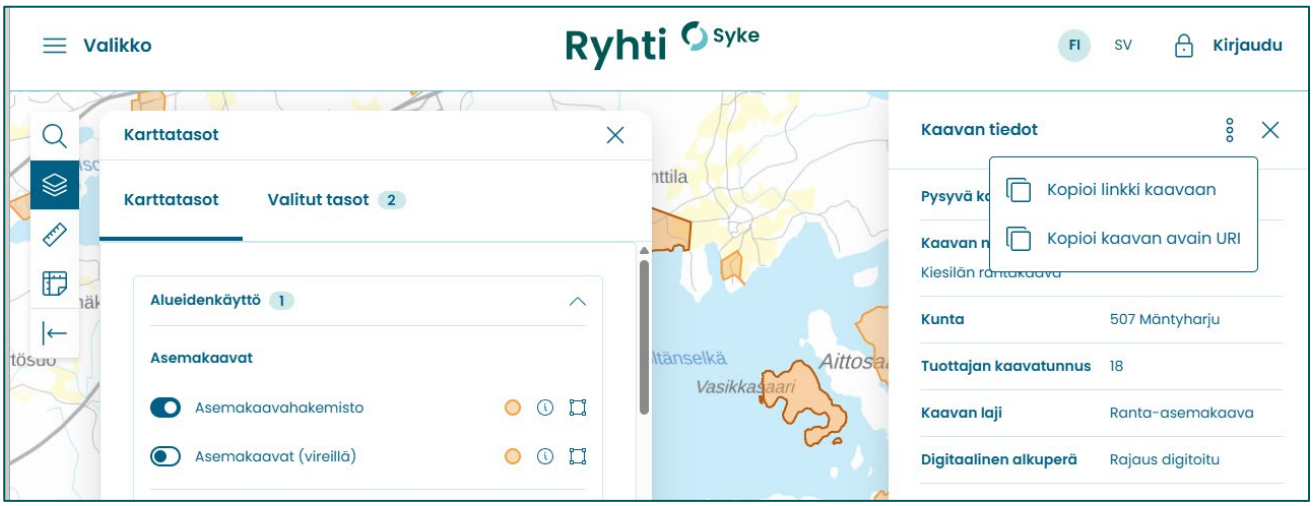

Kuva 27: Kuvakaappaus Ryhti-palvelun karttakäyttöliittymästä, valittuna asemakaavahakemisto ja haluttu kaava.

Toinen tapa muodostaa kaavan avain URI on hakea kaavan plankey kaavahakemistorajapinnalta ja muodostaa URI sen avulla. Kaavahakemistorajapinnalta voi hakea kumottavan kaavan plankeyn UUID-arvon. Esimerkiksi QGIS:n infopainikkeella voi hakea kaavan GUID/UUID-tunnisteen, joka syötetään JSON-tiedoston kumoutumistietoihin.
plan_key attribuutin arvo -->
"cancelledPlanUri": "https://uri.rakennetunymparistontietojarjestelma.fi/plan/fbd3788a-2c0d-47ea-99ce-0886a58afce6",

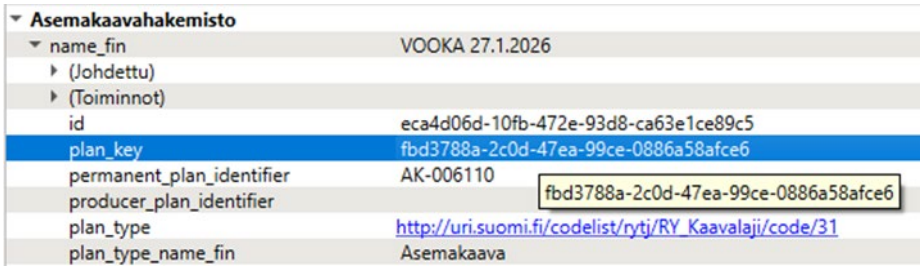

Kuva 28: QGIS-näkymä kaavahakemistoon, jossa on plan_key arvo.

Esimerkkitiedostoja kansiossa

UUSI_VOOKA-Kaava_vaiheen_aluerajaus.json
UUSI_AK_VOOKA_kumoaa_kaavan_kokonaan.json
UUSI_AK_VOOKA_kumoaa_kaavan_osittain.json
UUSI_YK_VOOKA_kumoaa_kaavan_kokonaan.json
UUSI_YK_VOOKA_kumoaa_kaavan_osittain.json

11. Uusi kaava kumoaa useamman kaavan kokonaan tai osittain

Lomakkeella kohtaan 5. tallennetaan JSON-tiedosto, jossa ovat mukana kumoutumistiedot kaikille kumottaville kaavoille. JSON-sanomassa pitää olla kumoutumistieto jokaiselle kumottavalle kaavalle.

Kansiossa ovat esimerkkitiedostot JSON-sanomasta kahden erillisen kaavan kumoamiseen yhdellä kaavalla.

Esimerkkitiedostot

UUSI_AK_VOOKA2_kumoaa_2kaavaa_kokonaanJAosittain.json
UUSI_YK_VOOKA2_kumoaa_2kaavaa_kokonaanJAosittain.json

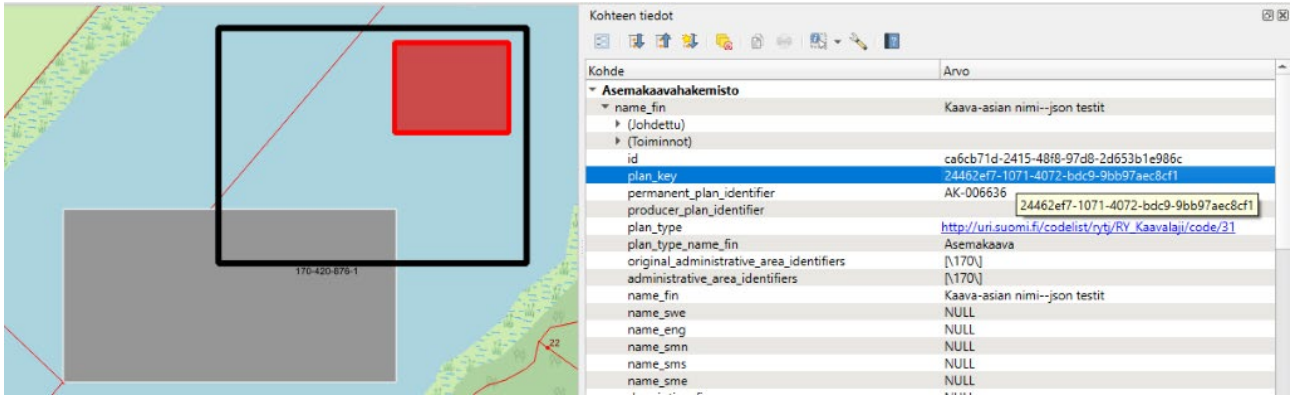

Kuva 29: Uusi VOOKA-kaava kumoaa kaksi alle jäävää VOOKA-kaavaa (osittain, kokonaan).

Kuvassa punaisella on kaava, joka kumoutuu kokonaan. JSON-tiedostossa kohta "cancelsEntirePlan": true.

Kuvassa harmaalla on kaava, joka kumoutuu osittain. JSON-tiedostossa kohta "cancelsEntirePlan": false.

Kopioi rajapinnalta planKey-attribuutin arvo osaksi JSON-tiedoston **"cancelledPlanUri"**-kohtaa. Katso esimerkki-JSON kuvasta 30.

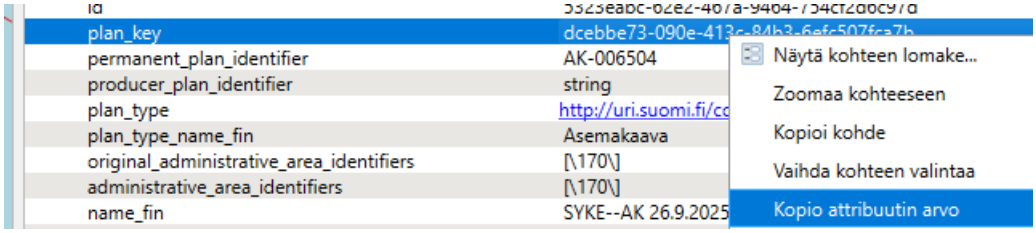

Kuva 30: Esimerkki plan_key:n kopioimisesta

Kaavaluokalle tallennetaan JSON-tiedosto, jossa Kumottavien kaavojen tiedot ovat pilkulla eroteltuna kumoutumistiedoissa { } -sisällä.


```
{
 "planKey": "46877e24-6cd0-4534-a863-755417bc9002",
 "lifeCycleStatus": "http://uri.suomi.fi/codelist/rytj/kaavaelinkaari/code/13",
 "legalEffectOfLocalMasterPlans": [
 "http://uri.suomi.fi/codelist/rytj/oikeusvaik_YK/code/1"
  ],
 "scale": 10000,
 "geographicalArea": {
 "srid": "3067",
 "geometry": {
 "type": "Polygon",
 "coordinates": [ 376895.413716607959941, 6670011.78399389795959 ], [
376895.413716608076356,  6670185.051267450675368 ], [ 377094.834540888376068,
6670185.051267450675368 ], [ 377094.834540888376068, 6670011.783993900753558 ], [
376895.413716607959941, 6670011.78399389795959 ] ] ]
  }
   },
 "planCancellationInfos": [
  {
   "planCancellationInfoKey": "efc58f2d-68b0-423b-b950-7c9e9f825b94",
   "cancelledPlanUri": "https://uri.rakennetunymparistontietojarjestelma.fi/plan/24462ef7-1071-
4072-bdc9-9bb97aec8cf1",
   "cancelsEntirePlan": true
    },
    {
   "planCancellationInfoKey": "f041f978-9fba-4e8d-820f-47b9491ec525",
   "cancelledPlanUri": "https://uri.rakennetunymparistontietojarjestelma.fi/plan/dcebbe73-090e-
413c-84b3-6efc507fca7b",
   "cancelsEntirePlan": false
    }
    ],
"periodOfValidity": {
"begin": "2025-11-13"
 },
 "approvalDate": "2025-03-17"
 }
```


Kuva 31: Esimerkki kaava-jsonista, jossa kumoutumistieto mukana. Vaaleansinisellä on korostettu kumottavan kaavan plankey.

12. Kaava on kumottu erillisellä päätöksellä

Jos kunta on kumonnut Ryhti-järjestelmään tallennetun kaavan erillisellä päätöksellä (eikä esimerkiksi kaavamuutoksella), kunnan tulee tallentaa uusi vaihe (*kumoutunut*) aiemmin tuotuun kaava-asiaan. Tällöin päätöksen nimi on *kaavan kumoaminen*, http://uri.suomi.fi/codelist/rytj/kaavpaatnimi/code/14.

12.1. Lisää uusi vaihe



Kuva 32: Kuvakaappaus Ryhti-palvelun lomakenäkymästä.

12.2. Elinkaarentila kumoutunut

Kuva 33: Elinkaarentilan valinta Ryhti-palvelun lomakenäkymässä.

12.3. Lisää vaiheen aluerajaus (sama kuin voimassa vaiheella)

Aluerajauksen lisääminen on selitetty aiemmissa luvuissa. Katso kuvat 15 ja 22.

12.4. Täytä päätöksen tiedot

Päätöksen nimi on *Kaavan kumoaminen*. Pakolliset tiedot päätökselle ovat päätöksen nimen lisäksi päätöspäivämäärä ja päättäjän laji. Pakolliset tiedot ovat lomakkeella merkittynä tähdellä.

Kun kaava kumotaan kokonaan päätöksellä, valitaan päätöksen nimeksi *14 kaavan kumoaminen*. Sen jälkeen näkyviin tulee laatikko, johon pitää tuoda kumoamistieto JSON-sanomana. Ryhti-järjestelmä päivittää kaavahakemiston niin, ettei kumottu kaava näy enää järjestelmässä.

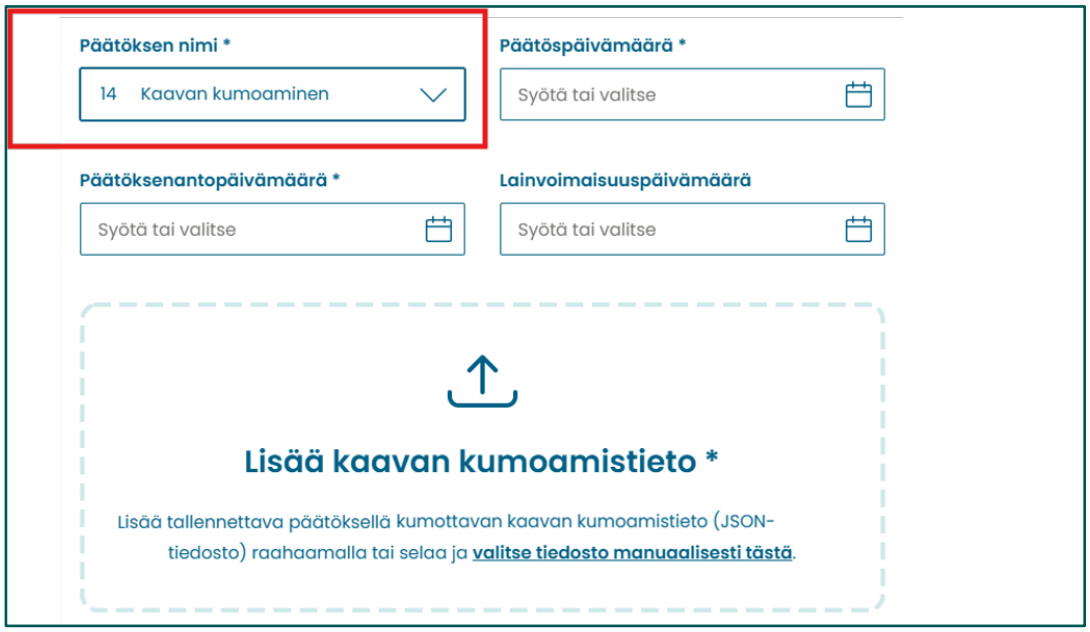

Kuva 34: Päätökseksi valitaan Kaavan kumoaminen.


```
{
  "planCancellationInfos": [
    {
      "planCancellationInfoKey": "a6910231-75dc-414c-a2b1-2a976aa8b7a7",
      "cancelledPlanUri": "https://uri.rakennetunymparistontietojarjestelma.fi/plan/7809c472-594b-44e1-99bd-6cc570138564",
      "cancelsEntirePlan": true
    }
  ]
}
```


Kuva 35: Kumoamistiedon JSON-sanoma

Esimerkkitiedosto

Kumoamistieto: *Päätös_kumoaminen_kokonaan_kumoamistieto_VOOKA.json*).